La bataille du secteur fortifié de Lille

Mai 1940

avant propos

Avant de commencer la lecture de cette brochure, revenons sur son origine.
Ce travail s'inscrit dans la continuité de notre ouvrage *L'histoire du secteur fortifié de Lille*.

Dans ce premier livre, nous avons présenté les fortifications et leur rôle dans la défense du Nord de la France. Cependant, un aspect essentiel restait encore peu développé : les combats eux-mêmes.

Cette brochure a donc pour objectif de retracer en détail ce que l'on peut appeler **la bataille du secteur fortifié de Lille**, un épisode méconnu de la campagne de France de 1940.

Brève, confuse et souvent éclipsée par les événements de Dunkerque et de la poche de Lille, cette bataille n'apparaît pas dans les ouvrages historiques. Pourtant, elle témoigne de la résistance des troupes alliées et de l'intensité des combats qui se sont déroulés le long de la frontière franco-belge.

Cette étude vise à redonner sa place à cet épisode oublié de l'histoire.

1.La préparation.

Après la grande guerre, la France et le Royaume-Uni ont deux visions différentes, la France sent le besoin de se protéger initialement de l'Italie fasciste de Mussolini puis de l'Allemagne nazie tandis que le royaume uni vise une méthode "d'apaisement". Les Britanniques ne veulent plus revivre la douleur de la grande guerre. Pendant des années le Royaume-Uni laisse l'allemagne faire pour éviter une nouvelle guerre destructrice comme par exemple lors de l'annexion des sudètes par l'allemagne en octobre 1938. Pendant ce temps, la France construit depuis 1928 la "Ligne Maginot", une succession de fortifications censée protéger la frontière Est et la frontière Alpine. En 1937, la belgique proclame sa neutralité, il est décidé en urgence de construire une ligne de fortification à la frontière franco-belge. Le projet est en partie soutenu par le ministre Édouard Daladier, cette ligne sera nommée "Ligne Daladier".

Insigne de la ligne Maginot.

2.L'agression !

Le premier septembre 1939, l'Allemagne lance une offensive contre la Pologne sans déclaration de guerre préalable. Pour répondre à l'attaque, la France et le Royaume-Uni déclarent la guerre à l'Allemagne. Au même moment, quelques troupes françaises sont lancées dans la Sarre pour tester les forces allemandes. Le 17 septembre 1939, l'URSS lance à son tour une invasion de la Pologne. L'état major Français comprend alors que le sort de la pologne est malheureusement scellé. Les troupes françaises présentes dans la Sarre se replient sur la ligne Maginot puis… plus aucun affrontement. C'est le début de la drôle de guerre ! En octobre 1939, l'armée Britannique débarque en France avec la British Expeditionary Force.

L'arrivée en France de la BEF. Photo : Imperial War Museum

3. Le plan Dyle

Le plan Dyle est un plan d'action adopté par la France et le Royaume-Uni en 1939. Il vise à faire face à une éventuelle attaque allemande à l'Ouest. Les chefs militaires français pensent alors que l'armée allemande passera principalement par la Belgique, comme lors de la Première Guerre mondiale. Le principe du plan Dyle consiste à faire avancer rapidement les armées françaises et britanniques en Belgique, afin d'établir une ligne de défense le long de la rivière Dyle, entre Anvers et Namur. Cette stratégie a pour objectif de protéger la Belgique, de défendre la France loin de ses frontières et d'éviter les destructions sur le territoire français.

Des soldats britanniques franchissent la frontière belge. Photo : Imperial War Museum.

4. La drôle de guerre.

Le terme “drôle de guerre” vient du mot Anglais “phoney war” (guerre bizard) et d’une mauvaise traduction en français qui devient “funny war” (drôle de guerre). Pendant la drôle de guerre, la vie des soldats est rythmée par l’attente.

Des soldats britanniques attendent dans une tranchée. Photo : Imperial War Museum.

Comme expliqué dans notre précédent livre, les soldats britanniques et français participent à la construction de pillboxes, de tranchées et d’obstacles antichars.

5. Une nouvelle agression.

Le 10 Mai 1940, l'allemagne envahit les pays du bénélux comme prévu par l'état major. Les troupes franco-britanniques franchissent la frontière pour prêter main-forte aux Belges.

LE SOIR

FILS SPÉCIAUX AVEC PARIS ET LONDRES

LE NOUVEAU CRIME HITLÉRIEN

L'Allemagne attaque la Belgique, la Hollande et le Luxembourg

La brutale agression n'a été précédée d'aucun ultimatum, d'aucune démarche diplomatique

La Belgique fait appel à la France et à l'Angleterre

Les troupes franco-britanniques sont en marche

Vive le Roi! Vive la Belgique!

Le crime allemand

L'AGRESSION

Attention aux parachutistes et aux saboteurs

Les attaques aériennes

Signaux d'alerte

Le Gouvernement décrète la mobilisation générale et l'état de siège

Un journal du 10 Mai 1940. ©les blockhaus lyssois.

Des soldats britanniques franchissent la frontière belge à herseaux. Photo : Imperial War Museum.

A leur arrivée en belgique, les soldats font face aux panzers allemands et aux bombardiers. Les soldats sont gênés par l'exode des civils, fuyant les bombes.

Le 13 Mai 1940, un événement inattendu se produit ! Les Allemands sont rentrés en France par les Ardennes ! Une région très peu fortifiée car selon les généraux français "Les chars allemands ne pourront pas passer par la forêt des Ardennes" pourtant, il y parviennent !

Il est donc décidé de se replier pour contre-attaquer. Malgré des résistances héroïques, les chars allemands arrivent à passer et foncent vers le nord.
Les positions en Belgique sont abandonnées et de nombreuses routes sont coupées.

Un soldat britannique fait sauter des explosifs à Louvain le 14 Mai. Photo : Imperial War Museum.

Peu à peu, les forces alliées se retirent de la Belgique.

Entre le 14 et 19 Mai, Tournai est bombardé, les britanniques abandonnent leurs matériels et dynamitent les ponts pour prendre position sur leurs fortifications de l'autre côté de la frontière.

Au même moment,à Cysoing, le 19 Mai, une colonne de chars britanniques se dirige vers la belgique, ils sont pris sous le feu et les bombes de l'aviation allemande, deux chars sont perdus et 4 morts sont à déplorer.

6. La bataille du Secteur Fortifié de Lille

Le **19 mai 1940**, la situation devient critique.
Dans les villages proches de la frontière, les habitants fuient précipitamment devant l'avancée allemande. Charrettes, bicyclettes et voitures surchargées envahissent les routes tandis que les bombardements obligent les civils à se jeter dans les fossés pour se protéger.

Combats dans la partie nord

En Mai, les allemands contournent les fortifications de la partie Armentières-Neuville en Ferrain. Le secteur étant en partie protégé par la Lys. Notons que des combats ont eu lieu entre les Royals Fusiliers et les troupes allemandes le 26 Mai.

Combats dans la partie centre

Le 24 Mai, des combats éclatent à Wattrelos notamment dans les plaines de beaulieu. Les soldats britanniques combattent pendant plusieurs jours dans les tranchées. Les blockhaus présents ne semblent pas avoir été utilisés.

Un blockhaus à Beaulieu ©les blockhaus lyssois.

Les combats à Wattrelos feront 31 victimes britanniques.

Le 25 Mai, les Allemands attaquent la ville de Tourcoing. Les britanniques opposent une résistance acharnée notamment au risquons-tout. Les soldats étaient des hommes de l'East Surrey Regiment, des *Buffs*, du Bedfordshire and Hertfordshire Regiment, des Lancashire Fusiliers et du Middlesex Regiment. Parmi eux, une équipe de trois fantassins du régiment des East Surreys se distingue particulièrement. Équipés d'un Bren Carrier (transporteur de troupes) ces hommes livrèrent un combat remarquable contre l'ennemi. Ils dévalent la rue du purgatoire tout en mitraillant les troupes ennemies. Un camion ennemi surgit et le bren carrier ouvre une nouvelle fois le feu.

Malgré leur détermination et une attaque initialement réussie, leur véhicule fut détruit par un canon antichar à une centaine de mètres et les trois hommes furent tués dans l'engagement. D'autres soldats, bien que courageux, furent blessés ou perdirent également la vie avant que les positions ne tombent.

Ce jour-là, douze soldats perdirent la vie dans les combats. Le conducteur du Bren Carrier, le Private Brian Waring, n'avait que 21 ans. L'un de ses compagnons d'armes, le Private Horace Roberts, n'en avait que 19. Aujourd'hui, un monument est visible au risquons-tout.

Un pillbox au risquons-tout ©les blockhaus lyssois.

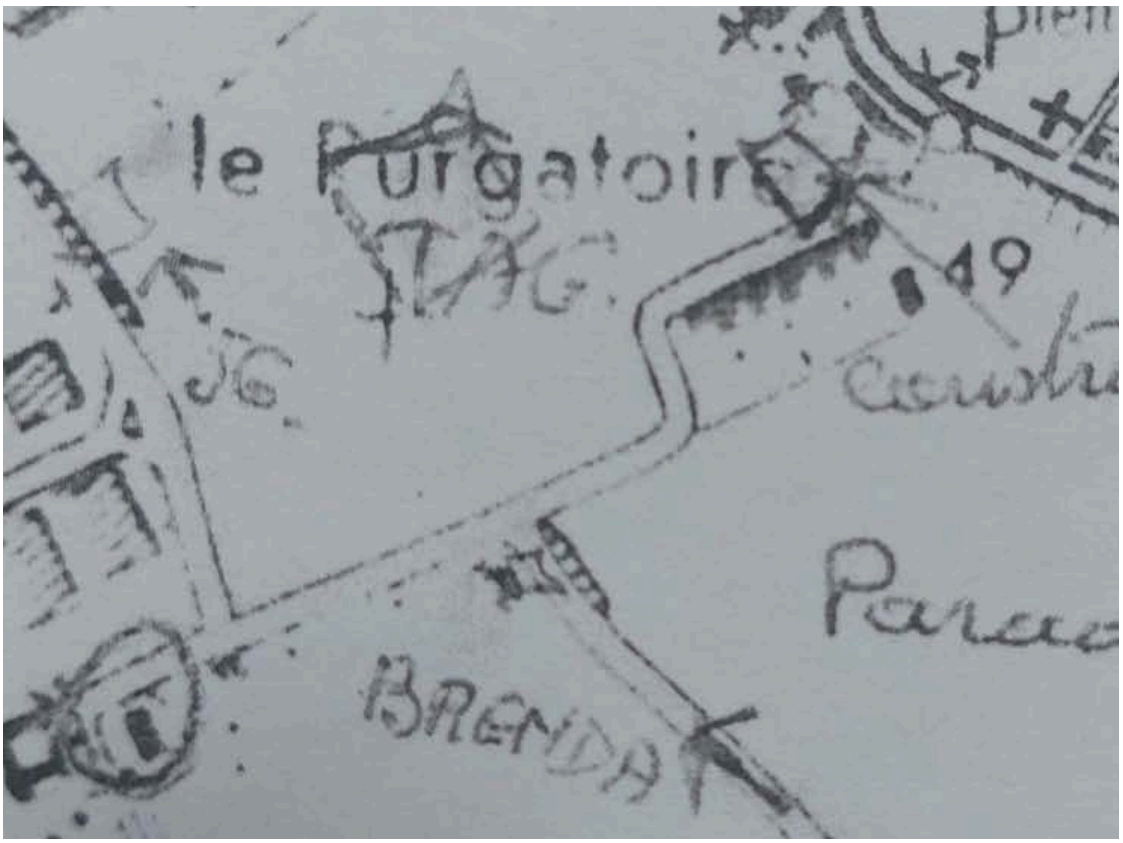

Plan de la rue du purgatoire en 1940.

Le monument du risquons-tout ©les blockhaus lyssois.

Le 27 Mai, les Britanniques sont contraints d'évacuer, à Leers, le carrefour de la rue victor hugo et de la rue de Lys sont minés. Les Allemands explosent sur celles-ci et la moitié de la rue victor hugo sera détruite. Le 28 Mai, Wattrelos est sous couleurs allemandes.

Combats dans la partie sud

Les combats dans la partie sud ont été très violents, à l'image du SF-Escaut. Les soldats sont harcelés jour et nuit par des assauts, l'aviation et l'artillerie allemande. Les Allemands franchissent la frontière depuis les communes avoisinant Tournai, entrant au sud de Cysoing par Wannehain.

À Cysoing, c'est le 5th Border Regiment qui tient la zone avant de se replier vers Lesquin le 26 mai. Le régiment est fréquemment bombardé par l'aviation ennemie.

Le 24 mai, le régiment observe une forte concentration d'ennemis et réagit en demandant des tirs d'artillerie défensifs sur toute la zone. Cette action réussit à repousser une attaque ennemie apparemment prévue.

Le lendemain matin, le 25 mai, la situation devient encore plus tendue. Des tireurs d'élite ennemis sont aperçus dans une maison et dans une botte de foin à proximité. L'artillerie est utilisée pour détruire la maison, tandis que le Capitaine T.P. Hetherington, de la Compagnie C, met le feu à la botte de foin.

26 mai (nuit) :
Le 5ème Bataillon commence à se déplacer, initialement en direction de Lesquin. Les Compagnies C et D sont laissées à Cysoing pour couvrir le retrait des autres troupes. Ensuite, ces deux compagnies se déplacent directement vers Le Bizet, au nord d'Armentières.

Le même jour, les Allemands attaquent ! Ils sont reçus par le feu du créneau nord du petit pillbox de la Pierre Plate, qui est rapidement neutralisé par une bombe d'un bombardier Stuka.

Le créneau nord du pillbox. ©les blockhaus lyssois.

L'intérieur du pillbox. ©les blockhaus lyssois.

Le pillbox du moulin foutry sera aussi endommagé par quelques obus de 20mm. Les faces Sud et Nord-Ouest sont criblés d'impacts

La face Sud.

Les Allemands sont aussi sous le feu du bloc de camphin. Ils mettront longtemps pour le neutraliser. Ils essaient de tirer sur le créneau de tir avec une pluie d'obus, des obus explosifs d'un assez gros calibre rentrent et explosent à l'intérieur.

La façade sud du bloc est rongée par les impacts d'obus. ©les blockhaus lyssois.

Le mur derrière le créneau de tir du bloc est endommagé par des obus explosifs. ©les blockhaus lyssois.

Les Allemands passent devant la façade nord du bloc et sont mitraillés par un créneau pour fusil mitrailleur. Les allemands ripostent et le réduisent au silence.

Le créneau pour fusil mitrailleur de la façade nord. ©les blockhaus lyssois.

Après avoir neutralisé le créneau pour F.M, les Allemands essaient de rentrer dans le bloc mais la porte est verrouillée et ils sont encore une fois sous le feu d'un créneau pour F.M (créneau ouest). ils sécurisent la porte en tirant sur le créneau ouest et à travers le créneau de la porte.

Des impacts sont visibles sur la porte. ©les blockhaus lyssois.

Le créneau ouest est abîmé. ©les blockhaus lyssois.

Ils tentent alors de faire sauter la porte de droite mais cela ne fera que la déformer.



La porte déformée. ©les blockhaus lyssois.

Après de rudes combats, le bloc est capturé. Les allemands continuent leur progression et les blockhaus sont peu à peu capturés. À proximité, le pillbox des six chemins tient bon en couvrant le fossé antichar ! Le pillbox est martelé d'impacts d’obus de 20mm.

La façade du pillbox.

Le créneau Est du pillbox de la couture sud n°1 ouvre le feu sur les allemands, il est neutralisé par des obus de 20mm Flak.

Des impacts sont visibles.

Le créneau nord ouvre ensuite le feu sur les troupes ennemies, un obus de gros calibre traverse alors le blockhaus par le créneau. Le blockhaus est mis hors de combat.

Le créneau.

L'intérieur.

Autour de Gruson, c'est le 5e bataillon du Manchester Regiment, appartenant à la 127e brigade commandée par le brigadier Ronald France. Cette unité prit position dans le secteur le 22 mai 1940 avec pour mission de tenir la ligne tandis que le Corps expéditionnaire britannique se repliait progressivement depuis l'Escaut.

Les défenses existantes offraient déjà une base solide. Une ligne antichar soigneusement aménagée était appuyée par des blockhaus et complétée par une position secondaire. Toutefois, une brèche fut rapidement découverte dans le fossé antichar. Les Royal Engineers s'employèrent aussitôt à la combler en disposant des mines antichars à intervalles réguliers, transformant ce point faible en obstacle redoutable pour toute tentative d'approche ennemie.

Le 23 mai, le calme fut troublé par l'apparition de plusieurs avions de reconnaissance allemands qui survolèrent les positions britanniques. Peu après, une bombe tomba sur une route minée située à l'est du dispositif. Le lendemain, les soldats poursuivent leurs travaux défensifs, creusant des emplacements de tir et renforçant leurs positions, tout en aidant à l'évacuation de civils restés dans la zone de combat.

Dans la journée du 24 mai, les premiers accrochages eurent lieu. Une patrouille allemande d'une trentaine d'hommes fut repérée à environ neuf cents mètres et prise sous le feu de la compagnie B. Peu après, la compagnie C ouvrit également le feu, tandis que des mouvements ennemis étaient signalés dans un bois situé à plus d'un kilomètre des positions britanniques. Trois mortiers furent alors dirigés vers cette zone afin de disperser les éléments adverses.

La riposte allemande ne tarda pas. Les blockhaus de première ligne furent prises pour cible et des obus de mortier lourds commencèrent à tomber sporadiquement autour des positions du bataillon. Au cours de la nuit, les Britanniques subirent leurs premières pertes sérieuses : un soldat fut tué et un officier gravement blessé lorsqu'un chef de patrouille marcha accidentellement sur une mine antichar.

Le 25 mai, la situation demeura relativement calme, bien que ponctuée de tirs de mortiers intermittents. Dans le ciel, un ballon d'observation allemand apparut, probablement chargé de repérer les positions britanniques pour guider l'artillerie lourde.

Malgré l’absence d’assaut d’envergure au cours de la journée, les positions britanniques furent soumises à de violents bombardements d’artillerie et à plusieurs attaques aériennes visant la ligne de blockhaus. Depuis leurs postes d’observation avancés, les soldats britanniques signalèrent d’importantes formations ennemies en mouvement.

Du côté allemand, la manœuvre était clairement définie. L’attaque menée contre les positions frontalières devait avant tout fixer sur place le Corps expéditionnaire britannique, tandis que l’effort principal progresserait vers Ypres, point de jonction stratégique entre les forces britanniques et belges.

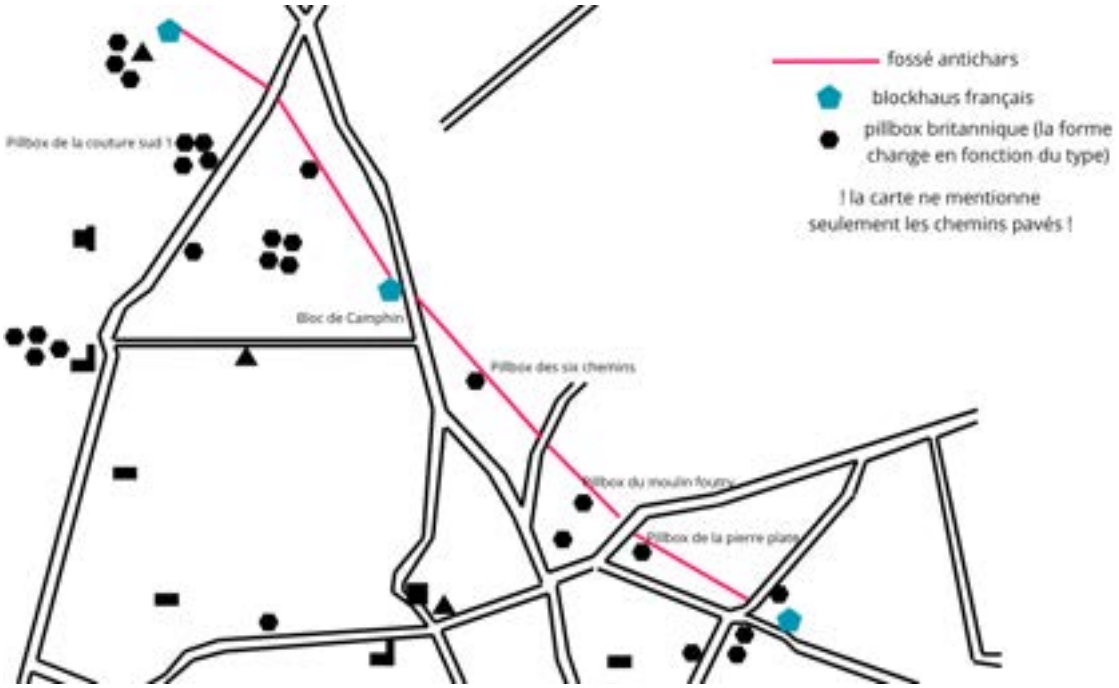

Carte des blockhaus ayant servi à ralentir les allemands dans le secteur de Cysoing.

Plus au sud, à Bachy, (Le 26 Mai), le bloc de la plaine sud est pris à partie. Le créneau sud (probablement armé d’un canon) est pris sous une pluie d’obus. Le bloc fait feu en direction du fossé antichar. Il sera vite capturé. Les soldats abandonnent leurs matériels dans les bois avoisinants et incendient le dépôt de ravitaillement anglais, installé dans la bourloire.

La façade sud du bloc. ©les blockhaus lyssois.

À Mouchin, des combats ont lieu, mais de faible intensité. Notons tout de même que le Bloc du marais de Bercu fut attaqué. Quelques impacts de balles sont visibles sur sa porte blindée et deux impacts d'obus sont visibles sur la façade Nord-Ouest.

Au même moment, le bloc d’Anstaing ouvre le feu par le créneau nord. Les Allemands ripostent avec un canon de 37mm. Après quelques échanges de tirs, les Britanniques abandonnent le bloc.

Le créneau pour canon du bloc d’Anstaing. ©les blockhaus lyssois.

Plus au nord, les Allemands passent par Baisieux puis Tressin. Le bloc gresart tire sur les ennemis avec son créneau Ouest. Les Allemands, surpris, tirent sur celui-ci à l'aide de canons de petit calibre. Mais la résistance du bloc est tenace, le créneau pour canon est réduit à néant mais le créneau pour F.M tire encore ! La face Ouest du bloc est martelée d’obus. Le bloc finit par être capturé.

Le créneau pour canon est fortement endommagé. ©les blockhaus lyssois.

Le créneau pour F.M. ©les blockhaus lyssois.

Le 28 Mai, les troupes franco-britanniques sont enfermées dans “la poche de lille” et plus au nord dans “la poche de Dunkerque”. À Lille, les soldats français opposent une résistance acharnée face aux troupes allemandes. Ils se retrouvent bloqués dans plusieurs poches autour de Lille et combattent à 40.000français contre 110.000allemands. Le 1er Juin 1940, les combats cessent par manque de munitions, les soldats ont contenu pas moins de 7 divisions allemandes mobilisés pour sécuriser la poche. Les allemands leurs rendent les honneurs militaires sur la place de Lille. Après la poche, le SF-Lille n'a plus aucune utilité. À Dunkerque, l’armée britannique sabordent leur matériel avant d'embarquer sur des bateaux pour rejoindre l'Angleterre. Tous les bateaux sont réquisitionnés pour secourir les soldats. Les britanniques sont défendus par des soldats Français et Belges. C’est l'opération dynamo. Après cette évacuation qui a duré du 26 Mai au 4 Juin, 338 226 soldats britanniques, français et belges sont évacués mais 80% du matériel britannique est perdu !

Les soldats attendent d’être évacués photo : Imperial War Museum

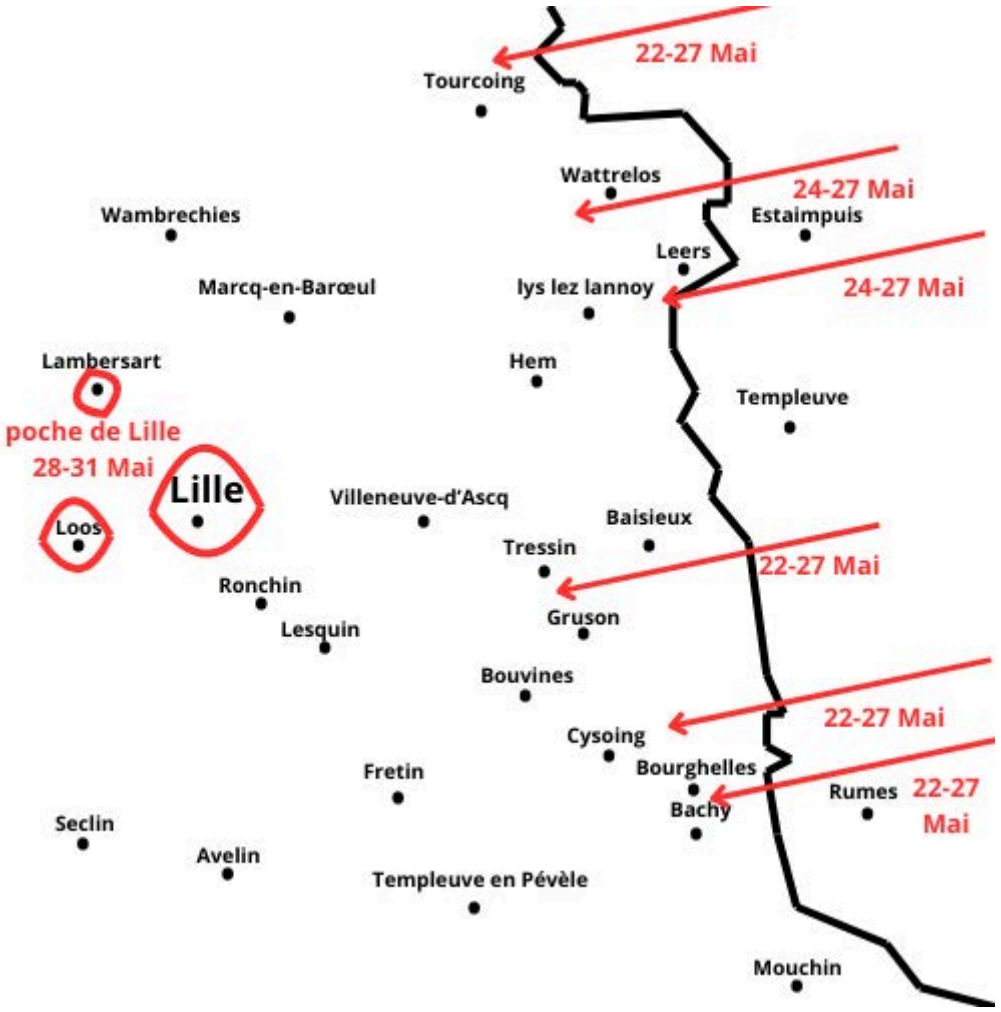

Carte des combats. ©les blockhaus lyssois.

7. Conclusion

Le secteur fortifié de Lille à été inutile ? Non ! Le SF-Lille faisait partie d'une tactique de défense de la frontière. Les causes de son inutilité viennent non pas de la tactique de fortification utilisée mais d'une erreur stratégique dans les Ardennes. Les généraux français auraient dû prévoir une attaque allemande par les Ardennes. Le SFL s'est retrouvé encerclé par les troupes allemandes et les soldats se sont retrouvés mobilisés plus au sud. De plus, seulement quelques blockhaus ont servi. La tactique employée sur le SFL est une tactique de flanquement imaginée pour couvrir une large zone et aider les autres blocs avoisinant, hors, les blocs ont été attaqués séparément et les combattants étaient dans des bloc éloignés de plusieurs kilomètres rendant inefficace les tirs de flanquements et créant des brèches au sein du dispositif. Il faut aussi que les combats héroïques qui se sont déroulés sont des combats de retardement pour contenir le plus d'ennemis afin d'aider leurs camarades à Dunkerque. Sans ces hommes qui se sont sacrifiés en tenant la ligne coûte que coûte, le rembarquement de Dunkerque aurait probablement échoué.

Souvenons-nous !

Table des matières

- La préparation : Page 3

- L'agression: Page 4

- Le plan Dyle : Page 5

- La drôle de guerre : Page 6

- Une nouvelle agression : Pages 7-9

- **La bataille du Secteur Fortifié de Lille :** Pages 10-29

- **Conclusion** : Page 30

Rédaction : Erwan Merlin

Abréviations utilisées :

Blockhaus : Structure de défense en béton armé, conçue pour résister aux tirs d'artillerie et abriter des troupes ou des armes.

Ligne Maginot : Système de fortifications construit par la France le long de ses frontières orientales et alpines après la Première Guerre mondiale, dans le but de se protéger contre une éventuelle attaque allemande.

Ligne Daladier : Ligne de fortifications construite en urgence à la frontière franco-belge après la proclamation de neutralité de la Belgique en 1937.

Drôle de guerre : Période de la Seconde Guerre mondiale (de septembre 1939 à mai 1940) caractérisée par une absence de combats majeurs sur le front occidental. Le terme vient de l'anglais "phoney war" (fausse guerre).

Corps expéditionnaire britannique (BEF) : Force militaire envoyée par le Royaume-Uni pour soutenir la France au début de la Seconde Guerre mondiale.

Secteur Défensif de Lille (SDL) / Secteur Fortifié de Lille (SFL) : Zone fortifiée le long de la frontière franco-belge, faisant partie de la ligne Maginot.

Pillbox : Terme britannique désignant un petit blockhaus.

Royals Engineers : Corps du génie de l'armée britannique, responsable de la construction et de la maintenance des fortifications.

FM (Fusil-Mitrailleur) : Arme automatique portative, plus légère qu'une mitrailleuse, utilisée pour le soutien d'infanterie.

Fossés antichars : Tranchées creusées pour gêner la progression des blindés.

Tranchées : Fossés creusés dans le sol pour offrir une protection aux soldats contre les tirs ennemis.

Oreillon : Pièce bétonnée ajoutée à un créneau pour protéger contre les tirs venant des côtés.

Créneau : Ouverture dans une fortification permettant de tirer tout en étant protégé.

Secteur Fortifié des Flandres / Secteur Fortifié de l'Escaut : Autres secteurs fortifiés faisant partie de la ligne Maginot.

"Gort Line" : Nom donné par les Britanniques à la ligne de défense le long de la frontière franco-belge.

Panzers : Terme allemand désignant les chars de combat.

Les sources :

Combats à Wattrelos :
https://www.ville-wattrelos.fr/la-seconde-guerre-mondiale#:~:text=Le%2015%20mai%201940%2C%20des,dans%20la%20plaine%20de%20Beaulieu.

Combats à cysoing :
https://2ndww.blogspot.com/2013/08/the-border-regiments-5th-battalion-in.html?utm

Bachy en mai 1940 : https://www.mairie-bachy.fr/Mai-1940-a-Bachy.html

Mentions légales et Droit d’auteur.

Contact : lesblockhauslyssois@gmail.com ou sur notre site internet : https://lesblockhauslyssois.fr

Propriété Intellectuelle :

L'ensemble des textes, illustrations, photographies dans ce livre gratuit sont la propriété exclusive du groupe les blockhaus lyssois ou de leurs auteurs respectifs. Toute reproduction, représentation, modification, publication, adaptation, ou exploitation, partielle ou totale, de ces éléments, par quelque procédé que ce soit, sans l'autorisation écrite préalable du groupe les blockhaus lyssois, est strictement interdite. Les photos utilisées qui n'appartiennent pas au groupe les blockhaus lyssois (ex : photos d’époques) sont des photos libres de droits trouvées sur internet dont la source est signalée en dessous. Certains passages sont la propriété d’autres personnes, merci de ne pas les utiliser sans leur autorisation.

Gratuité :

Ce livre est proposé gratuitement à des fins d'information et de diffusion culturelle. Il ne peut en aucun cas être vendu. Il est interdit de reproduire et/ou commercialiser ce livre.

Respect des propriétaires et des lieux :

Les photos prises dans des terrains privés ont été publiées avec l’accord de leur propriétaire, merci de ne pas les déranger. Veuillez aussi respecter les blockhaus pour ceux étant dans des espaces accessibles.

Merci pour votre compréhension